Teamprojekt

Adaktylos Leonidas Odysseas, Baumgartner Vincent Vitez, Neda Nikkhousarighiyeh, Alexander Grath

M2 Low-fidelity Prototypen

universität wien

Inhaltsverzeichnis

1 Data Feed Idee **2**
1.1 Menü / Optionen . . . 3
1.2 Themenauswahl . . . 3
1.3 Datenset . . . 3
1.4 Ziel . . . 3

2 Karten Idee **4**
2.1 Karte . . . 4
2.2 Downloads . . . 4
2.3 Einstellungen . . . 4

3 Story Explorer – Idee **4**
3.1 Startseite . . . 4
3.2 Themenübersichtsseite . . . 4
3.3 Story-Ansicht . . . 4
3.4 Einstellungen . . . 4
3.5 Ziel . . . 5

4 Wien in Zahlen – Idee **5**
4.1 Grundkonzept . . . 5
4.2 Personalisierter Feed . . . 5
4.3 Aufbau der Fact Sheets . . . 5
4.4 Unterstützung beim Verstehen von Visualisierungen . . . 5
4.5 Voting und Frageportal . . . 5
4.6 Ziel der Umsetzung . . . 5

5 ”Data Feed Prototyp **6**

6 Prototyp Karte **7**

7 Startseite **7**

8 Downloads **7**

9 Einstellungen **7**

10 Story Explorer – Prototyp **7**
10.1 Screen 1 – Startseite . . . 8
10.2 Screen 2 – Themenübersicht . . . 8
10.3 Screen 3 – Story-Ansicht . . . 8
10.4 Screen 4 – Einstellungen . . . 8

11 Wien in Zahlen – Prototyp **8**

12 ”Data Feed Anpassung **11**
12.1 Primäre Personas . . . 11
12.2 Sekundäre Personas . . . 11
12.3 Negative Persona . . . 12

13 Anpassung Leonidas **13**

14 Story Explorer – Anpassung **13**
14.1 Primäre Personas . . . 13
14.2 Sekundäre Personas . . . 13
14.3 Negative Persona . . . 13

15 Anpassung Vincent **13**

16 Evaluierung Alexander **14**

17 Evaluierung Leonidas **14**

18 Story Explorer – Evaluierung **14**

19 Evaluierung Vincent **14**

20 Arbeitsverteilung **15**
20.1 Kreativitätstechniken 15
20.2 Aufteilung 15

21 KI Nutzung **15**

1 Data Feed Idee

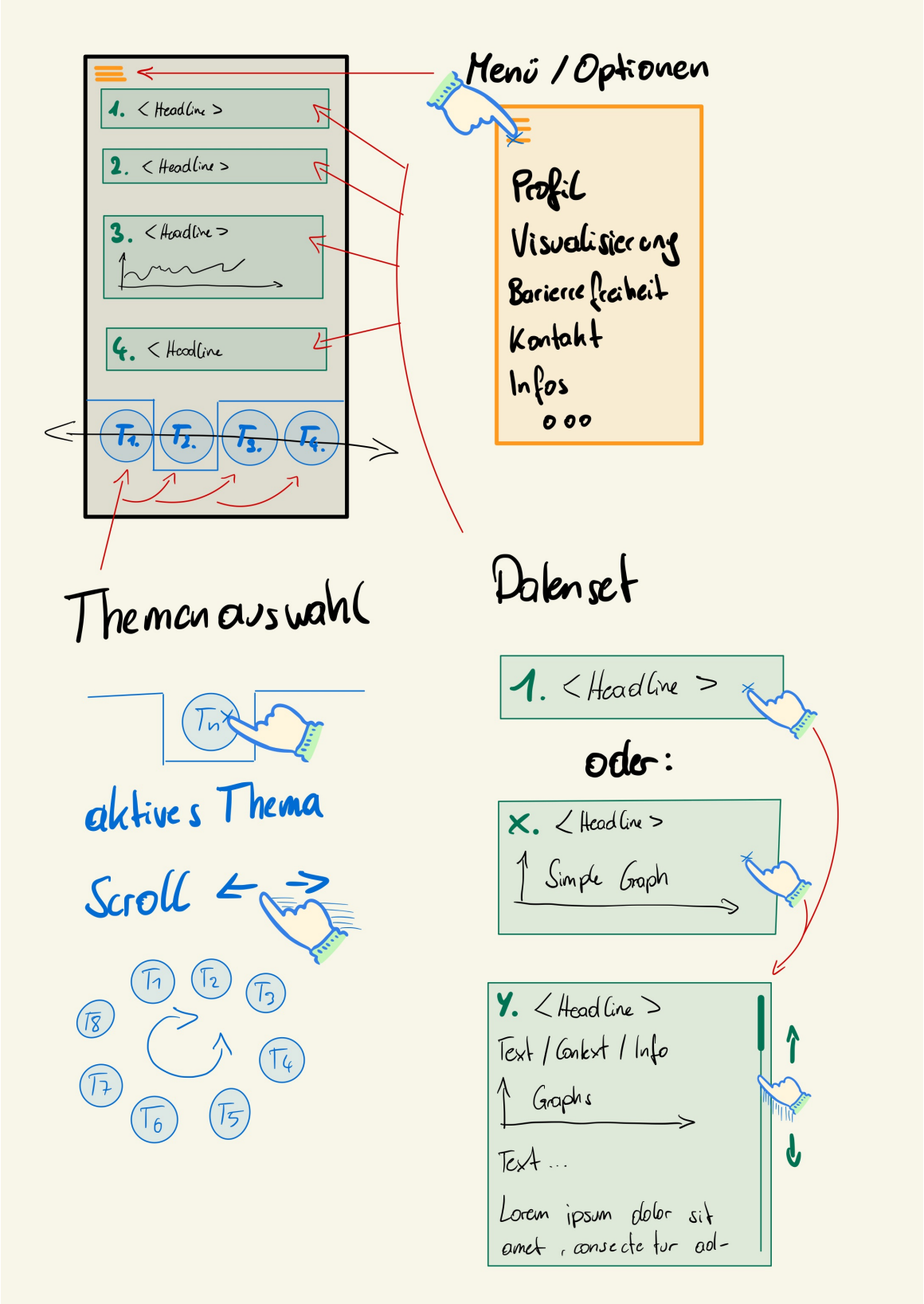

Wurde mit Goodnotes erstellt.

Abbildung 1: Napkin Drawing Idee zur App

Die *Data Feed*-App soll es Nutzern spielerisch einfach machen, Daten und Informationen zu konsumieren. Prinzipiell schauen wir uns einiges von anderen, erfolgreichen Apps und Plattformen ab. Vor allem von Social-Media-Apps wie Twitter, Facebook und vielen anderen. Eine generelle Gemeinsamkeit dieser Apps ist der sogenannte *Feed*. Eine endlose Liste an Beiträgen, die, meist automatisch, für den Nutzer zusammengestellt werden.

1.1 Menü / Optionen

In einem simplen Burgermenü sind alle wichtigen Einstellungen und Optionen vorhanden.

Profileinstellungen, Informationen zur Kontaktaufnahme (Impressum) und für viele Nutzer ganz wichtig: Barrierefreiheit. Um Daten darzustellen, werden oft Farben verwendet. Diese sollten einstellbar sein, dass auch farbenblinde alles unterscheiden können. Kontrast, Darstellungsgröße und Darstellungsformen sollte man hier anpassen können. Jeder sollte diese App verwenden und genießen können.

1.2 Themenauswahl

Die Nutzer:innen können am unteren Ende des Bildschirms durch die Themen scrollen. Dieser Bereich lässt sich nach links oder rechts bewegen. Sichtbare Themen können auch direkt angeklickt werden. Das aktuelle Thema wird farblich hinterlegt, um zu verdeutlichen, was ausgewählt wurde. Mögliche Themen sind Finanzen, Mobilität, Umwelt und soziale Themen. Es wird auch spaßigere Themen / Kategorien geben. Ein Beispiel wären Karten, die z.B.: alle Bäume in Wien darstellen.

Die Themen sind in einem Karussell, durch welches man endlos im Kreis (links und rechts) scrollen kann.

1.3 Datenset

Die individuellen Datensets werden wie bei anderen Plattformen dargestellt. Anstelle von einem Tweet oder Facebook-Post ist es hier ein einzelner Datensatz. Jeder Datensatz oder Beitrag bekommt eine Überschrift. Wenn es sich ergibt, kann auch ein kleines Bild oder ein kleines Diagramm angezeigt werden.

Wird ein einzelner Beitrag angeklickt, dann öffnet sich dieser. Nun kann man durch den ganzen Beitrag scrollen. Je nach Datensatz bekommt man eine schriftliche Erklärung, um den Inhalt verstehen zu können. Es könnten weiterführende Beiträge verlinkt sein, zusätzlicher Kontext zur Verfügung gestellt werden und zu guter Letzt der Kernpunkt der App die Darstellung der Daten. Auch wieder abhängig vom Datensatz kommen verschiedene Visualisierungsmethoden zum Einsatz. Es kann eine einfache Tabelle sein, ein Bild, Graphen oder auch Karten.

1.4 Ziel

Das Ziel der App ist es, den Nutzern eine einfache und entspannte Möglichkeit zu bieten, die Daten und Informationen zu konsumieren. Es sollte unterhaltsam, einfach und freundlich sein. Eine Alternative zum sogenannten ”doomscrolling”bei der man auch noch etwas lernen kann.

2 Karten Idee

Die *Karten*-App stellt die Datenpunkte geographisch auf einer Karte da. So können Nutzer Datensätze entdecken, die in ihrem eigenen Leben eine große Rolle spielen. Die Datensätze sollten mit Pins auf der Karte dargestellt werden, die geklickt werden können.

2.1 Karte

Eine Karte ermöglicht es Nutzern,

2.2 Downloads

Nutzer sollen Datensätze, die sie besonders interessant finden oder auf die sie Online Zugriff haben können herunterladen können.

2.3 Einstellungen

LOREM IPSUM

3 Story Explorer – Idee

Die Story-Explorer-App verfolgt einen themenbasierten Ansatz zur Visualisierung offener Daten der Stadt Wien. Im Mittelpunkt steht die Idee, Datensätze nicht isoliert darzustellen, sondern sie in Form von kurzen, verständlichen *Datenstorys* aufzubereiten. Die App richtet sich bewusst an Nutzer:innen ohne technischen Hintergrund und setzt auf eine klare, intuitive Struktur mit vier zentralen Bereichen.

3.1 Startseite

Die Startseite begrüßt Nutzer:innen mit dem Titel „Wien erkundenünd bietet zwei Einstiegsmöglichkeiten: eine Suchleiste für gezielte Anfragen sowie eine Themenauswahl in Form eines Rasters. Die vier Hauptthemen **Umwelt**, **Mobilität**, **Wohnen** und **Bezirke** ermöglichen eine schnelle thematische Navigation. Unterhalb der Themenauswahl befindet sich der Bereich „Schnell entdecken", der beliebte und aktuelle Datenstorys als farblich hervorgehobene Schaltflächen vorschlägt – etwa *„Luftqualität in Wien 2026"* oder *„Bäume pro Bezirk"*. Am unteren Bildschirmrand befindet sich eine persistente Navigationsleiste mit den Bereichen *Start*, *Themen*, *Saved* und *Profil*, die auf allen Seiten sichtbar bleibt.

3.2 Themenübersichtsseite

Nach der Themenauswahl gelangen Nutzer:innen zur Themenübersichtsseite, die alle verfügbaren Datensätze des gewählten Themas als scrollbare Liste anzeigt. Jeder Eintrag zeigt einen Titel sowie eine kurze Beschreibung (*Dataset Subtitle*) und kann per Radiobutton ausgewählt werden. Beispiele für das Thema *Umwelt* sind: Luftqualität im Alltag, Grünflächen pro Bezirk, Parks in meiner Nähe, Trinkbrunnen & Wasserstellen Wien sowie der Baumkataster Wien. Über einen **Filter**-Button können die Ergebnisse nach *Bezirk* und *Zeitraum* eingeschränkt werden, um gezielt relevante Datensätze zu finden.

3.3 Story-Ansicht

Die Story-Ansicht ist das Herzstück der App. Sie präsentiert den ausgewählten Datensatz strukturiert mit Titel, Quellenangabe (z. B. *„Quelle: Stadt Wien"*) und einer interaktiven Visualisierung. Ein eigener Abschnitt „Kurz erklärtlliefert eine verständliche Erläuterung der dargestellten Daten – beispielsweise eine Beschreibung von PM2.5-Feinstaubpartikeln und ihrer gesundheitlichen Relevanz bei der Story *„Luftqualität im Alltag"* Über zwei klar beschriftete Schaltflächen können Inhalte **exportiert** oder **geteilt** werden, was die Weiterverwendung der Daten erleichtert.

3.4 Einstellungen

Das Einstellungsmenü ist über das Profil in der Navigationsleiste erreichbar und bietet Nutzer:innen personalisierte Optionen. Die verfügbaren Einträge umfassen *Profil*, *Visualisierung*, *Barrierefreiheit*, *Kontakt* sowie *Infos & Quellen*. Besonders hervorzuheben ist der Bereich **Barrierefreiheit**, über den Farbschemata und Darstellungsgrößen angepasst werden können, sodass die App auch für farbenblinde oder seheingeschränkte Nutzer:innen zugänglich ist.

3.5 Ziel

Ziel der Story-Explorer-App ist es, Open Data der Stadt Wien niederschwellig und ansprechend zu vermitteln. Durch die Kombination aus thematischer Navigation, kurzen Erklärungen und klaren Visualisierungen soll die App dazu beitragen, dass Bürger:innen informierte Entscheidungen treffen und ein besseres Verständnis für ihre Stadt entwickeln können.

4 Wien in Zahlen – Idee

4.1 Grundkonzept

Die Idee des Low-Fidelity-Prototyps *Wien in Zahlen* ist ein personalisierter Open-Data-Feed für die Stadt Wien. Die App soll nicht wie ein klassisches Datenportal funktionieren, in dem viele Datensätze gleichzeitig angezeigt werden. Stattdessen erhalten Nutzer:innen regelmäßig kurze und verständlich aufbereitete Datenbeiträge in Form von Fact Sheets. Dadurch verbindet die App Elemente einer News-App mit den Möglichkeiten eines Open-Data-Portals.

4.2 Personalisierter Feed

Zu Beginn der Nutzung wählen die Nutzer:innen Themen aus, die sie besonders interessieren, zum Beispiel Umwelt, Wohnen, Mobilität oder Energie. Auf Basis dieser Auswahl wird ein persönlicher Feed erstellt. In diesem Feed erscheinen kurze Karten mit aktuellen oder interessanten Datenbeiträgen zur Stadt Wien. Jede Karte gibt einen ersten Überblick und führt bei Interesse zu einem ausführlicheren Fact Sheet. So können Nutzer:innen selbst entscheiden, welche Inhalte sie genauer ansehen möchten.

4.3 Aufbau der Fact Sheets

Ein Fact Sheet enthält eine kurze Erklärung des Themas, eine einfache Datenvisualisierung, die verwendete Datenquelle, einen Vergleich sowie den Abschnitt *Was bedeutet das?*. Dieser Abschnitt ist besonders wichtig, weil er die zentrale Aussage der Daten in Alltagssprache erklärt. Die Nutzer:innen sollen nicht nur Zahlen sehen, sondern auch verstehen, welche Bedeutung diese Zahlen für Wien und den Alltag in der Stadt haben.

4.4 Unterstützung beim Verstehen von Visualisierungen

Ergänzend gibt es bei jeder Visualisierung ein *Grafik verstehen*-Element mit einem Fragezeichen. Wenn dieses angeklickt wird, öffnet sich eine kurze Erklärung zur jeweiligen Grafik, zum Beispiel wie ein Balkendiagramm gelesen wird. Dadurch unterstützt die App auch Menschen, die wenig Erfahrung mit Datenvisualisierungen oder Statistiken haben.

4.5 Voting und Frageportal

Zusätzlich enthält *Wien in Zahlen* ein Voting-System. Damit können Nutzer:innen abstimmen, welche Themen oder Datenfragen in Zukunft aufbereitet werden sollen. Ein Frageportal ermöglicht es außerdem, eigene Fragen zur Stadt Wien einzureichen. Dadurch wird die App nicht nur zu einem Informationsangebot, sondern auch zu einem Mitmach-Format.

4.6 Ziel der Umsetzung

Die Umsetzung ist sinnvoll, weil sie Open Data niedrigschwellig, personalisiert und alltagsnah vermittelt. Komplexe Daten werden in kleine, verständliche Einheiten übersetzt, wodurch mehr Menschen einen Zugang zu städtischen Informationen erhalten und sich besser mit Entwicklungen in Wien auseinandersetzen können.

5 ”Data Feed Prototyp

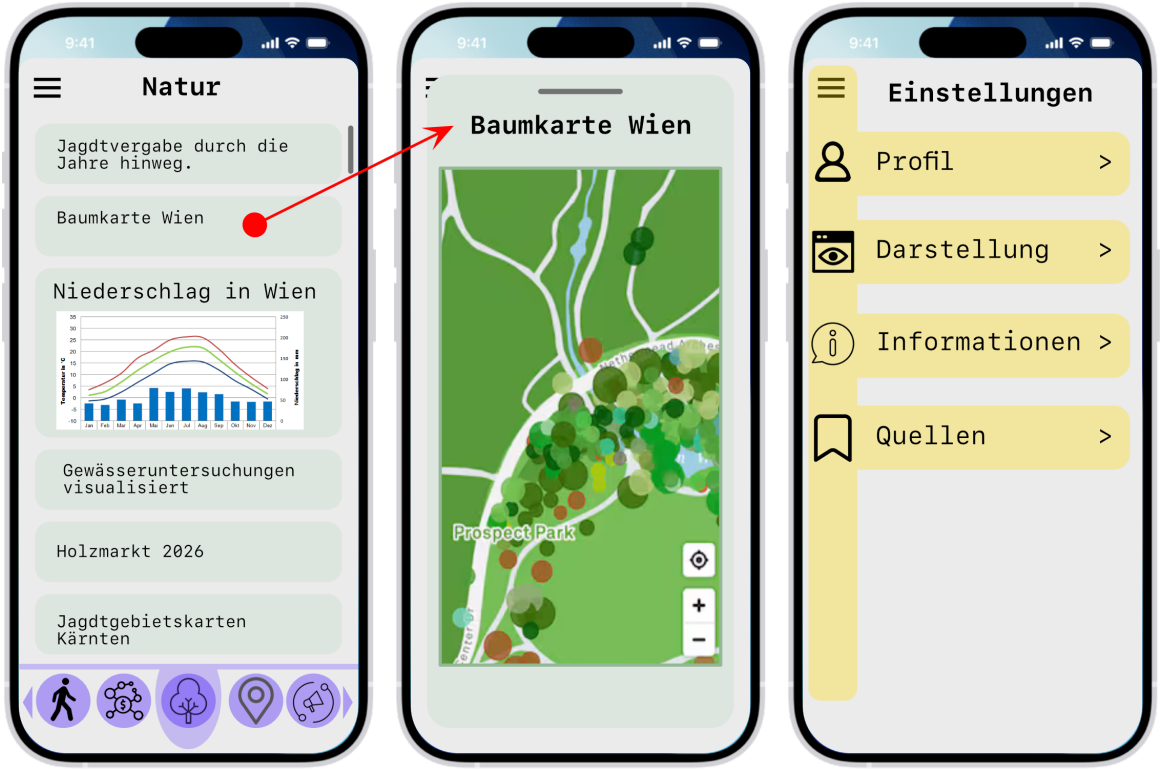

Abbildung 2: Prototyp zur ”Data FeedÄpp

Der Prototyp wurde mit Affinity Designer 2 erstellt. Bilder wurden aus öffentlich zugänglichen Quellen entnommen und teilweise bearbeitet. Die Icons sind alle von svgrepo, einer für SVG-Vektor und Icons mit einer offenen Lizenz. Die Fonts wurden von Apples Entwickler-Seite entnommen.

Im Prototyp wurde die Idee verfeinert und ist visuell besser dargestellt. Da *Einfachheit* ein Kernpunkt dieser Idee ist, ist auch die App sehr simpel. Auf der ersten Seite kann man die Themen wählen und bekommt direkt Inhalte präsentiert. Klickt man auf einen der Posts, vergrößert sich dieser. Streicht man nach unten, wird dieser wieder geschlossen. Ein Klick auf das Burgermenü öffnet die Einstellungen. Hier wurde alles in übergreifende Kategorien sortiert.

Die im Post dargestellte Karte wäre im Hintergrund via der Google-Maps API implementiert und erlaubt es, die Karte mit den (vermutlich) bereits vorhandene Kenntnisse des Nutzers zu bedienen.

Als Erweiterung zur Idee ist auch die Option dazugekommen dass man einstellen kann, von welcher Quelle die Daten bezogen werden. Bzw. werden die Nutzer hier auch über die verwendeten Quellen genauer informiert.

6 Prototyp Karte

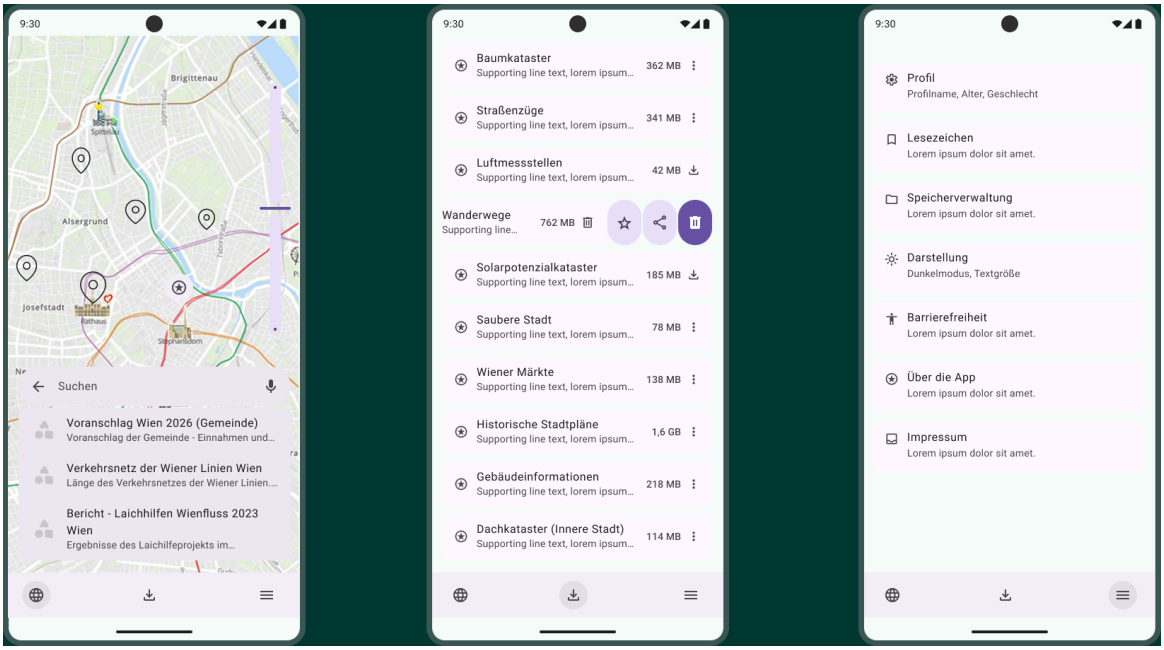

Abbildung 3: Prototyp zur ”KartenÄpp

Der Prototyp wurde mit Figma und dem Material 3 Design Kit von Google erstellt. Die Karte ist ein Screenshot vom Stadtplan der Stadt Wien.

7 Startseite

Die Startseite bietet drei Einstiegsmöglichkeiten. Eine Karte mit Pins die ausgewählt werden können, ein Suchfeld um nach Stichworten zu suchen und frühere Suchresultate. Die früheren Suchresultate verstecken sich automatisch, wenn man die Karte oder das Suchfeld bedient und können wieder aufgerufen werden, indem das Suchfeld nach oben gezogen wird.

8 Downloads

In den Downloads können Datensätze heruntergeladen, angesehen, geteilt, zu Lesezeichen hinzugefügt und wieder vom Gerät gelöscht werden. Die Datensätze selber werden in für die Datensätze passenden externen Apps (z.B. einem PDF Leser) geöffnet.

9 Einstellungen

In den Einstellungen können Profileinstellungen angepasst, Lesezeichen und Speicher verwaltet und zwischen Hell- und Dunkelmodus gewechselt werden. Man kann auch Informationen über die App und das Impressum einsehen.

10 Story Explorer – Prototyp

Der Prototyp der Story-Explorer-App wurde als digitaler Low-fidelity-Prototyp mit Balsamiq erstellt und zeigt die vier zentralen Screens der App sowie deren Interaktionsfluss.

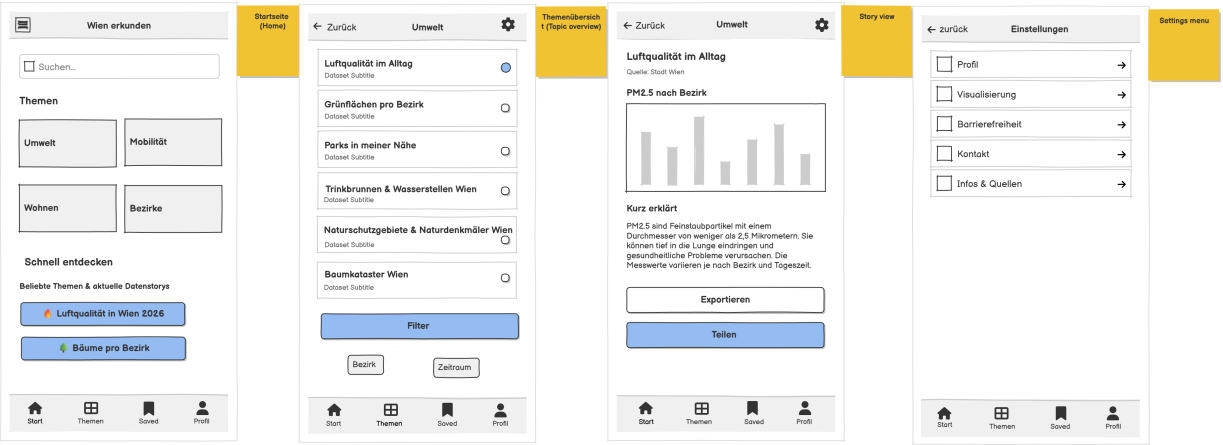

Abbildung 4: Low-fidelity Prototyp der Story-Explorer-App, erstellt mit Balsamiq

10.1 Screen 1 – Startseite

Die Startseite bietet zwei Einstiegsmöglichkeiten: eine Suchleiste für gezielte Anfragen sowie eine thematische Auswahl mit vier Kategorien (Umwelt, Mobilität, Wohnen, Bezirke). Der Bereich „Schnell entdeckenßchlägt beliebte Datenstorys direkt vor, sodass Nutzer:innen ohne Umwege zu relevanten Inhalten gelangen. Eine persistente Navigationsleiste am unteren Rand bleibt auf allen Screens sichtbar.

10.2 Screen 2 – Themenübersicht

Nach der Themenauswahl erscheint eine scrollbare Liste aller verfügbaren Datensätze zum gewählten Thema. Jeder Eintrag zeigt Titel und eine kurze Beschreibung. Ein **Filter**-Button ermöglicht die Einschränkung nach Bezirk und Zeitraum. Die Auswahl eines Datensatzes erfolgt über einen Radiobutton und führt direkt zur Story-Ansicht.

10.3 Screen 3 – Story-Ansicht

Die Story-Ansicht zeigt den ausgewählten Datensatz mit Titel, Quellenangabe und einer Visualisierung in Form eines Balkendiagramms. Der Abschnitt „Kurz erklärtlliefert eine verständliche Erläuterung der Daten in einfacher Sprache – etwa eine Beschreibung von PM2.5-Feinstaubpartikeln und ihrer gesundheitlichen Relevanz. Zwei Schaltflächen ermöglichen das Exportieren und Teilen der Inhalte.

10.4 Screen 4 – Einstellungen

Das Einstellungsmenü listet alle personalisierbaren Optionen übersichtlich auf: Profil, Visualisierung, Barrierefreiheit, Kontakt sowie Infos & Quellen. Jeder Eintrag ist über einen Pfeil-Button erreichbar. Besonders der Bereich Barrierefreiheit ermöglicht Anpassungen für seheingeschränkte Nutzer:innen.

Die Interaktion folgt einem linearen, klaren Ablauf: Thema wählen → Datensatz auswählen → Story lesen. Dieser bewusst einfache Navigationsfluss reduziert die kognitive Last und macht die App auch ohne Einführung bedienbar.

11 Wien in Zahlen – Prototyp

Der Low-Fidelity-Prototyp *Wien in Zahlen* zeigt anhand von drei Screens den grundlegenden Ablauf der App-Nutzung. Im ersten Screen beginnt die Interaktion mit einer Themenauswahl. Nutzer:innen sehen den Einstieg in die App und können auswählen, welche Themenbereiche sie besonders interessieren. Zur Auswahl stehen zum Beispiel Umwelt, Wohnen, Mobilität oder Energie. In dem dargestellten Beispiel sind die Themen Umwelt und Wohnen ausgewählt. Diese Auswahl ist wichtig, weil sie die Grundlage für den späteren personalisierten Feed bildet. Nachdem die Nutzer:innen ihre Interessen festgelegt haben, klicken sie auf den Button *Meinen Feed erstellen* und gelangen zum nächsten Screen.

Abbildung 5: Themenauswahl im Prototyp

Der zweite Screen zeigt den personalisierten Feed mit dem Titel *Dein Wien Radar*. Hier werden die zuvor ausgewählten Themen sichtbar aufgegriffen. Der Feed enthält kurze Karten mit Datenbeiträgen, die zu den Interessen der Nutzer:innen passen. Beispiele dafür sind Beiträge wie *Wie grün ist dein Bezirk?* oder *Mietpreise steigen in mehreren Bezirken*. Jede Karte gibt einen kurzen Einstieg in ein Datenthema und kann angetippt werden. Durch diese Interaktion gelangen Nutzer:innen zum passenden Fact Sheet, in dem das Thema genauer erklärt wird.

Zusätzlich bietet der Feed Zugänge zum Voting und zum Frageportal. Dadurch können Nutzer:innen nicht nur Inhalte konsumieren, sondern auch mitbestimmen, welche Themen oder Datenfragen in Zukunft aufbereitet werden sollen.

Abbildung 6: Personalisierter Feed mit Datenbeiträgen

Der dritte Screen zeigt ein geöffnetes Fact Sheet. In diesem Beispiel gehört es zum Themenbereich Umwelt und trägt den Titel *Fakt der Woche: Wie grün ist dein Bezirk?*. Das Fact Sheet vertieft den Datenbeitrag aus

dem Feed. Es enthält eine kurze Erklärung des Themas, eine einfache Visualisierung, eine Datenquelle, einen Vergleich und den Abschnitt *Was bedeutet das?*. Dieser Abschnitt fasst die wichtigste Aussage der Daten in verständlicher Alltagssprache zusammen.

Bei der Visualisierung gibt es außerdem ein *Grafik verstehen*-Element. Über dieses Element können Nutzer:innen eine kurze Erklärung öffnen, die beschreibt, wie die Grafik gelesen werden kann. Insgesamt zeigen die drei Screens eine klare Navigation vom Einstieg über den personalisierten Feed bis hin zum detaillierten Fact Sheet. Der Prototyp macht damit deutlich, wie offene Daten schrittweise, verständlich und nutzer:innenorientiert vermittelt werden können.

Abbildung 7: Fact Sheet mit Visualisierung und Erklärung

12 ”Data Feed Anpassung

12.1 Primäre Personas

Benjamin, Leah und Ralph nutzen die App sehr aktiv für ihr Hobby, Bildung und Beruf. Einen lockereren und einfachen Ansatz zur Datendarstellung werden sie sicher wertschätzen, aber sie wollen vermutlich mehr. Um PPower Usernëin besseres Erlebnis zu bieten, wird eine Suchfunktion mit Filtern eingebaut. Standardmäßig kann man mit dieser das aktuell gewählte Thema durchsuchen, es gibt aber auch weitere Optionen wie Filter, Quellen und ob man z.B.: Den Text oder nur den Titel durchsuchen will.

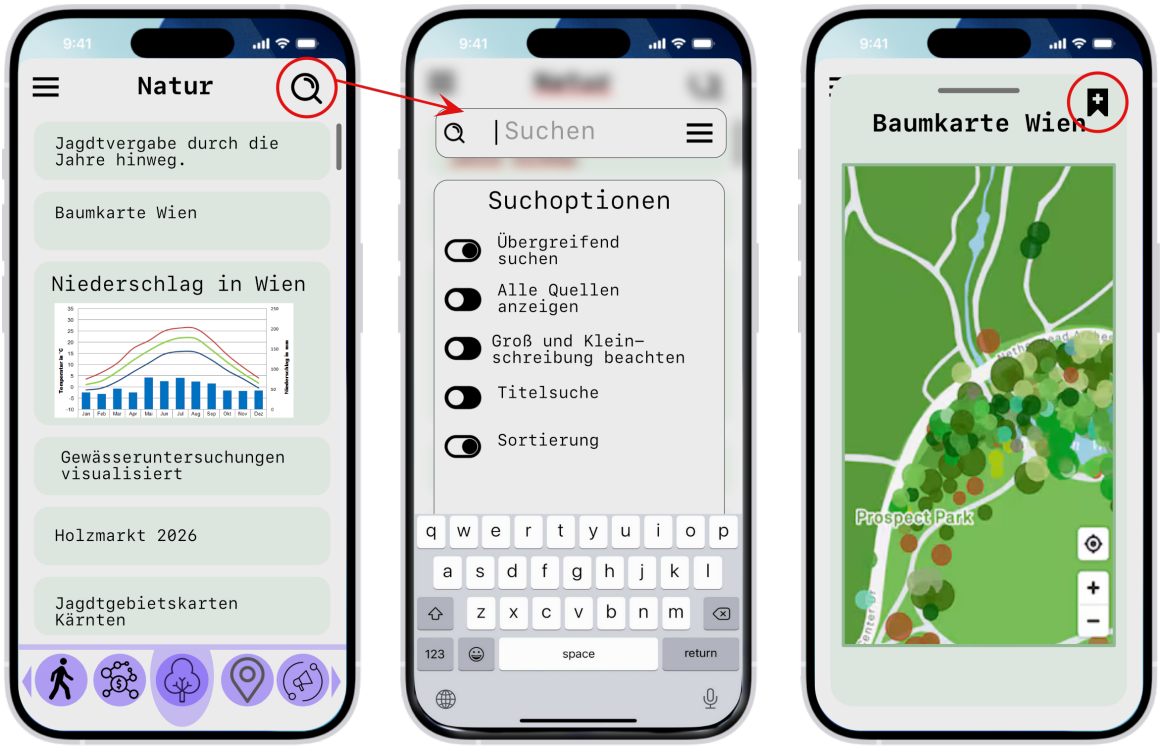

Abbildung 8: Erweiterung für Primäre Nutzer

In die rechte obere Ecke der Hauptseite wird ein Lupensymbol hinzugefügt. Wird dieses angeklickt, dann wird die Suchleiste eingeblendet und der Hintergrund unscharf gemacht. Die Tastatur öffnet sich automatisch und man kann sofort tippen. Durch Klicken außerhalb der Suchleiste wird die Suche beendet. Wird das Burgermenü angeklickt, dann öffnen sich die weiteren Einstellungen. Hier können die Suchparameter angepasst werden.

Bei jedem Post wird an die rechte obere Ecke ein LLesezeichenSymbol platziert. Hiermit können die Nutzer den Post für später speichern.

12.2 Sekundäre Personas

Luca, unser Repräsentant der sekundären Personas, ist ein Nutzer, der die App nicht oft nutzt. Während der Nutzung gibt es zwar ein Ziel, aber innerhalb der App bei unseren Daten wird nichts spezifisch genutzt. Für die sekundären Nutzer werden zwei Dinge hinzugefügt. Erstens wird noch vor der Auswahl der Themen ein weiterer Unterpunkt hinzugefügt: die Daten des Tages/Woche. Hier wird den Nutzern ein aktueller und interessanter Post vorgeschlagen. Zusätzlich gibt es noch eine Zufallssuche, hier kann man auf Knopfdruck einen zufälligen Post heraussuchen.

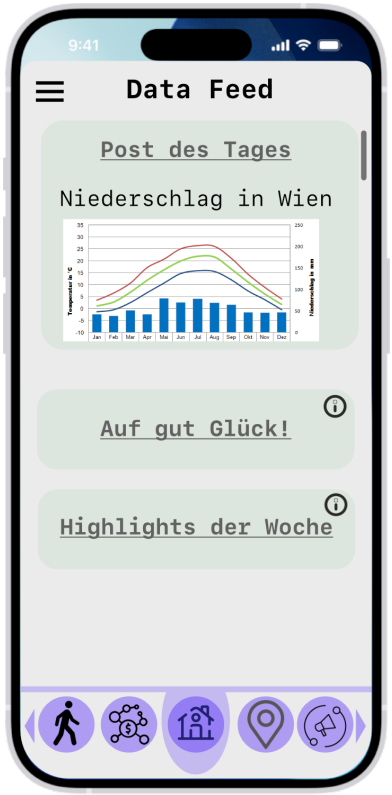

Abbildung 9: Erweiterung für Sekundäre Nutzer

12.3 Negative Persona

Die negative Persona ist jemand, der die dargestellten Daten zweckentfremden will und damit die Meinung anderer manipulieren will. In einer weniger extremen Darstellung eines negativen Nutzers könnte doch auch jemand versuchen, die Daten entweder falsch auszulegen oder sogar die Daten selber zu verändern. Innerhalb der App / der UI gibt es hier weniger zu tun. Eher ist es wichtiger, die API und App selbst mit guten Sicherheitsgrundlagen zu programmieren. Zusätzlich müssen die rechtlichen Grundlagen gut geklärt sein, wo und wie die Daten weiterverwendet werden dürfen (Lizenzen etc.). Seitens der Quellen muss es auch klar sein, dass wir keine Verantwortung für die Richtigkeit oder auch den Inhalt der Datensätze übernehmen.

13 Anpassung Leonidas

Lorem ipsum dolor sit amet, consectetuer adipiscing elit. Ut purus elit, vestibulum ut, placerat ac, adipiscing vitae, felis. Curabitur dictum gravida mauris. Nam arcu libero, nonummy eget, consectetuer id, vulputate a, magna. Donec vehicula augue eu neque. Pellentesque habitant morbi tristique senectus et netus et malesuada fames ac turpis egestas. Mauris ut leo. Cras viverra metus rhoncus sem. Nulla et lectus vestibulum urna fringilla ultrices. Phasellus eu tellus sit amet tortor gravida placerat. Integer sapien est, iaculis in, pretium quis, viverra ac, nunc. Praesent eget sem vel leo ultrices bibendum. Aenean faucibus. Morbi dolor nulla, malesuada eu, pulvinar at, mollis ac, nulla. Curabitur auctor semper nulla. Donec varius orci eget risus. Duis nibh mi, congue eu, accumsan eleifend, sagittis quis, diam. Duis eget orci sit amet orci dignissim rutrum.

Nam dui ligula, fringilla a, euismod sodales, sollicitudin vel, wisi. Morbi auctor lorem non justo. Nam lacus libero, pretium at, lobortis vitae, ultricies et, tellus. Donec aliquet, tortor sed accumsan bibendum, erat ligula aliquet magna, vitae ornare odio metus a mi. Morbi ac orci et nisl hendrerit mollis. Suspendisse ut massa. Cras nec ante. Pellentesque a nulla. Cum sociis natoque penatibus et magnis dis parturient montes, nascetur ridiculus mus. Aliquam tincidunt urna. Nulla ullamcorper vestibulum turpis. Pellentesque cursus luctus mauris.

14 Story Explorer – Anpassung

Der Prototyp wurde gezielt an die in Meilenstein 1 definierten Personas und Nutzergruppen angepasst. Nachfolgend werden die wesentlichen Designentscheidungen den jeweiligen Zielgruppen zugeordnet.

14.1 Primäre Personas

Benjamin (technikaffiner Student): Für diese Persona wurde eine Filterfunktion nach Bezirk und Zeitraum in der Themenübersicht ergänzt. So können erfahrene Nutzer:innen gezielt nach spezifischen Datensätzen suchen und die Ergebnisse einschränken, ohne durch irrelevante Inhalte scrollen zu müssen.

Leah (Content Creatorin): Die Schaltflächen „Teilen” und „Exportieren” wurden bewusst prominent in der Story-Ansicht platziert. Damit können Visualisierungen einfach in sozialen Netzwerken geteilt oder für Blogbeiträge exportiert werden – ohne zusätzliche Schritte.

Ralph (beruflicher Nutzer): Für diese Persona wurde eine klare Quellenangabe direkt unter dem Datensatztitel eingebaut. Dies gewährleistet Transparenz über die Datenherkunft und stärkt das Vertrauen in die Datenqualität – ein zentrales Kriterium für die berufliche Nutzung.

14.2 Sekundäre Personas

Luca (Gelegenheitsnutzer): Der Bereich „Schnell entdecken” auf der Startseite ermöglicht einen direkten Einstieg ohne Vorkenntnisse. Der Abschnitt „Kurz erklärt” in der Story-Ansicht übersetzt komplexe Daten in verständliche Sprache und macht die App auch für nicht-technische Nutzer:innen zugänglich.

14.3 Negative Persona

Für die negative Persona – Nutzer:innen, die Daten missbräuchlich weiterverwenden oder falsch auslegen könnten – wurden folgende Maßnahmen im Design berücksichtigt: Jeder Datensatz enthält eine explizite Quellenangabe sowie einen Hinweis auf die Lizenz der verwendeten Open-Data-Quellen. Damit wird klar kommuniziert, dass die Verantwortung für korrekte Weiterverwendung bei den Nutzer:innen liegt und die App keine Haftung für die Richtigkeit der Rohdaten übernimmt.

15 Anpassung Vincent

Lorem ipsum dolor sit amet, consectetuer adipiscing elit. Ut purus elit, vestibulum ut, placerat ac, adipiscing vitae, felis. Curabitur dictum gravida mauris. Nam arcu libero, nonummy eget, consectetuer id, vulputate a, magna. Donec vehicula augue eu neque. Pellentesque habitant morbi tristique senectus et netus et malesuada fames ac turpis egestas. Mauris ut leo. Cras viverra metus rhoncus sem. Nulla et lectus vestibulum urna fringilla ultrices. Phasellus eu tellus sit amet tortor gravida placerat. Integer sapien est, iaculis in, pretium quis, viverra ac, nunc. Praesent eget sem vel leo ultrices bibendum. Aenean faucibus. Morbi dolor nulla, malesuada eu, pulvinar at, mollis ac, nulla. Curabitur auctor semper nulla. Donec varius orci eget risus. Duis nibh mi, congue eu, accumsan eleifend, sagittis quis, diam. Duis eget orci sit amet orci dignissim rutrum.

Nam dui ligula, fringilla a, euismod sodales, sollicitudin vel, wisi. Morbi auctor lorem non justo. Nam lacus libero, pretium at, lobortis vitae, ultricies et, tellus. Donec aliquet, tortor sed accumsan bibendum, erat ligula aliquet magna, vitae ornare odio metus a mi. Morbi ac orci et nisl hendrerit mollis. Suspendisse ut massa. Cras nec ante. Pellentesque a nulla. Cum sociis natoque penatibus et magnis dis parturient montes, nascetur ridiculus mus. Aliquam tincidunt urna. Nulla ullamcorper vestibulum turpis. Pellentesque cursus luctus mauris.

16 Evaluierung Alexander

Lorem ipsum dolor sit amet, consectetuer adipiscing elit. Ut purus elit, vestibulum ut, placerat ac, adipiscing vitae, felis. Curabitur dictum gravida mauris. Nam arcu libero, nonummy eget, consectetuer id, vulputate a, magna. Donec vehicula augue eu neque. Pellentesque habitant morbi tristique senectus et netus et malesuada fames ac turpis egestas. Mauris ut leo. Cras viverra metus rhoncus sem. Nulla et lectus vestibulum urna fringilla ultrices. Phasellus eu tellus sit amet tortor gravida placerat. Integer sapien est, iaculis in, pretium quis, viverra ac, nunc. Praesent eget sem vel leo ultrices bibendum. Aenean faucibus. Morbi dolor nulla, malesuada eu, pulvinar at, mollis ac, nulla. Curabitur auctor semper nulla. Donec varius orci eget risus. Duis nibh mi, congue eu, accumsan eleifend, sagittis quis, diam. Duis eget orci sit amet orci dignissim rutrum.

Nam dui ligula, fringilla a, euismod sodales, sollicitudin vel, wisi. Morbi auctor lorem non justo. Nam lacus libero, pretium at, lobortis vitae, ultricies et, tellus. Donec aliquet, tortor sed accumsan bibendum, erat ligula aliquet magna, vitae ornare odio metus a mi. Morbi ac orci et nisl hendrerit mollis. Suspendisse ut massa. Cras nec ante. Pellentesque a nulla. Cum sociis natoque penatibus et magnis dis parturient montes, nascetur ridiculus mus. Aliquam tincidunt urna. Nulla ullamcorper vestibulum turpis. Pellentesque cursus luctus mauris.

17 Evaluierung Leonidas

Lorem ipsum dolor sit amet, consectetuer adipiscing elit. Ut purus elit, vestibulum ut, placerat ac, adipiscing vitae, felis. Curabitur dictum gravida mauris. Nam arcu libero, nonummy eget, consectetuer id, vulputate a, magna. Donec vehicula augue eu neque. Pellentesque habitant morbi tristique senectus et netus et malesuada fames ac turpis egestas. Mauris ut leo. Cras viverra metus rhoncus sem. Nulla et lectus vestibulum urna fringilla ultrices. Phasellus eu tellus sit amet tortor gravida placerat. Integer sapien est, iaculis in, pretium quis, viverra ac, nunc. Praesent eget sem vel leo ultrices bibendum. Aenean faucibus. Morbi dolor nulla, malesuada eu, pulvinar at, mollis ac, nulla. Curabitur auctor semper nulla. Donec varius orci eget risus. Duis nibh mi, congue eu, accumsan eleifend, sagittis quis, diam. Duis eget orci sit amet orci dignissim rutrum.

Nam dui ligula, fringilla a, euismod sodales, sollicitudin vel, wisi. Morbi auctor lorem non justo. Nam lacus libero, pretium at, lobortis vitae, ultricies et, tellus. Donec aliquet, tortor sed accumsan bibendum, erat ligula aliquet magna, vitae ornare odio metus a mi. Morbi ac orci et nisl hendrerit mollis. Suspendisse ut massa. Cras nec ante. Pellentesque a nulla. Cum sociis natoque penatibus et magnis dis parturient montes, nascetur ridiculus mus. Aliquam tincidunt urna. Nulla ullamcorper vestibulum turpis. Pellentesque cursus luctus mauris.

18 Story Explorer – Evaluierung

Lorem ipsum dolor sit amet, consectetuer adipiscing elit. Ut purus elit, vestibulum ut, placerat ac, adipiscing vitae, felis. Curabitur dictum gravida mauris. Nam arcu libero, nonummy eget, consectetuer id, vulputate a, magna. Donec vehicula augue eu neque. Pellentesque habitant morbi tristique senectus et netus et malesuada fames ac turpis egestas. Mauris ut leo. Cras viverra metus rhoncus sem. Nulla et lectus vestibulum urna fringilla ultrices. Phasellus eu tellus sit amet tortor gravida placerat. Integer sapien est, iaculis in, pretium quis, viverra ac, nunc. Praesent eget sem vel leo ultrices bibendum. Aenean faucibus. Morbi dolor nulla, malesuada eu, pulvinar at, mollis ac, nulla. Curabitur auctor semper nulla. Donec varius orci eget risus. Duis nibh mi, congue eu, accumsan eleifend, sagittis quis, diam. Duis eget orci sit amet orci dignissim rutrum.

Nam dui ligula, fringilla a, euismod sodales, sollicitudin vel, wisi. Morbi auctor lorem non justo. Nam lacus libero, pretium at, lobortis vitae, ultricies et, tellus. Donec aliquet, tortor sed accumsan bibendum, erat ligula aliquet magna, vitae ornare odio metus a mi. Morbi ac orci et nisl hendrerit mollis. Suspendisse ut massa. Cras nec ante. Pellentesque a nulla. Cum sociis natoque penatibus et magnis dis parturient montes, nascetur ridiculus mus. Aliquam tincidunt urna. Nulla ullamcorper vestibulum turpis. Pellentesque cursus luctus mauris.

19 Evaluierung Vincent

Lorem ipsum dolor sit amet, consectetuer adipiscing elit. Ut purus elit, vestibulum ut, placerat ac, adipiscing vitae, felis. Curabitur dictum gravida mauris. Nam arcu libero, nonummy eget, consectetuer id, vulputate a,

magna. Donec vehicula augue eu neque. Pellentesque habitant morbi tristique senectus et netus et malesuada fames ac turpis egestas. Mauris ut leo. Cras viverra metus rhoncus sem. Nulla et lectus vestibulum urna fringilla ultrices. Phasellus eu tellus sit amet tortor gravida placerat. Integer sapien est, iaculis in, pretium quis, viverra ac, nunc. Praesent eget sem vel leo ultrices bibendum. Aenean faucibus. Morbi dolor nulla, malesuada eu, pulvinar at, mollis ac, nulla. Curabitur auctor semper nulla. Donec varius orci eget risus. Duis nibh mi, congue eu, accumsan eleifend, sagittis quis, diam. Duis eget orci sit amet orci dignissim rutrum.

Nam dui ligula, fringilla a, euismod sodales, sollicitudin vel, wisi. Morbi auctor lorem non justo. Nam lacus libero, pretium at, lobortis vitae, ultricies et, tellus. Donec aliquet, tortor sed accumsan bibendum, erat ligula aliquet magna, vitae ornare odio metus a mi. Morbi ac orci et nisl hendrerit mollis. Suspendisse ut massa. Cras nec ante. Pellentesque a nulla. Cum sociis natoque penatibus et magnis dis parturient montes, nascetur ridiculus mus. Aliquam tincidunt urna. Nulla ullamcorper vestibulum turpis. Pellentesque cursus luctus mauris.

20 Arbeitsverteilung

Da die Angaben sehr oft genau so viele Unterpunkte/Themen etc. verlangt, wie es Leute in der Gruppe gibt, ist die gerechte Arbeitsaufteilung sehr einfach. Jeder macht seinen Teil und für die Abgabe wird alles zusammengefasst.

20.1 Kreativitätstechniken

Wir haben mit klassischem Brainstorming begonnen und sind dann zur Collective-Notebook Variante übergegangen. Wir haben uns mithilfe von Discord und unserem GitHub-Repository ausgetauscht und gemeinsam kollaboriert.

20.2 Aufteilung

Die Idee, Prototyp, Anpassung und Evaluierung wurde von jedem einmal einzeln gemacht. Wir haben uns über Discord ausgetauscht und gegenseitig informiert / Feedback gegeben.
Der Discord Server und das GitHub-Repository wurde von Adaktylos Leonidas Odysseas erstellt. Das gemeinsame LaTeX Projekt wurde von Alexander Grath erstellt.

21 KI Nutzung

Im Rahmen dieses Meilensteins wurde künstliche Intelligenz unterstützend eingesetzt.

Neda Nikkhousarighiyeh: Die Texte der Abschnitte *Story Explorer – Idee*, *Story Explorer – Prototyp* und *Story Explorer – Anpassung* wurden mithilfe eines KI-Sprachmodells grammatikalisch und sprachlich überarbeitet. Inhalt, Konzept und Ideen wurden vollständig selbst erarbeitet.

Literatur